TIME DE DESIGN · BO-E / AIA · NOVEMBRO 2026

Claude no Figma: 16 telas entregues em 2 PBIs

O Claude lê a PBI, parte das telas que já existem no projeto e monta as novas direto no arquivo, seguindo o nosso padrão visual. O designer revisa e ajusta em vez de desenhar do zero.

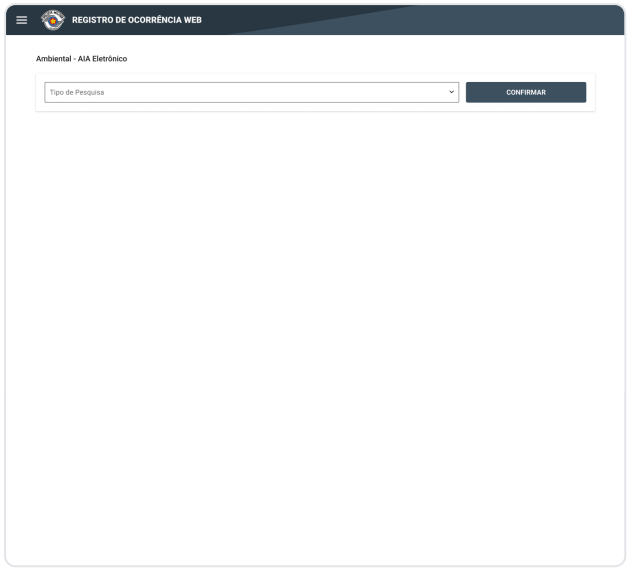
16	2	8–16 h
telas no Figma	PBIs atendidas (93729 e 95903)	de produção manual evitadas

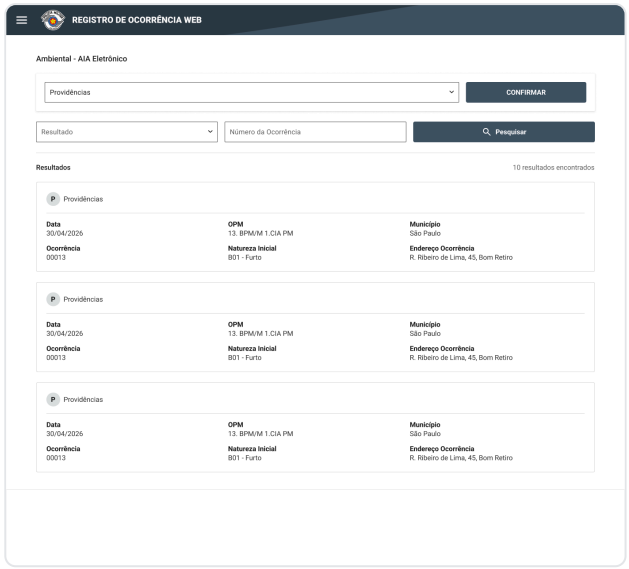
Estimativa com base na média do time de 30 min a 1 h por tela feita manualmente. Não inclui o tempo de leitura e interpretação das PBIs, que também cai bastante.

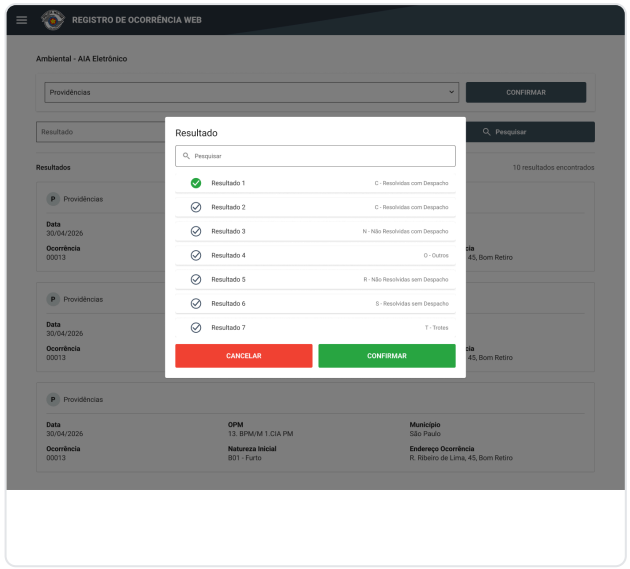
PBI 93729 · 6 TELAS

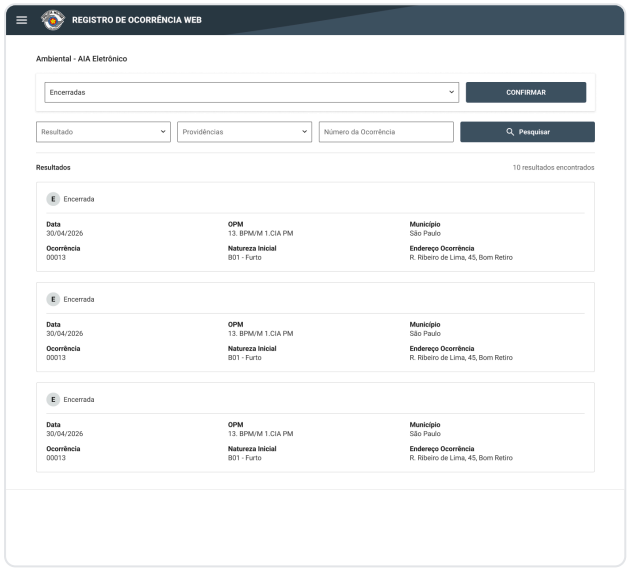
Filtros de pesquisa para Providências e Encerradas

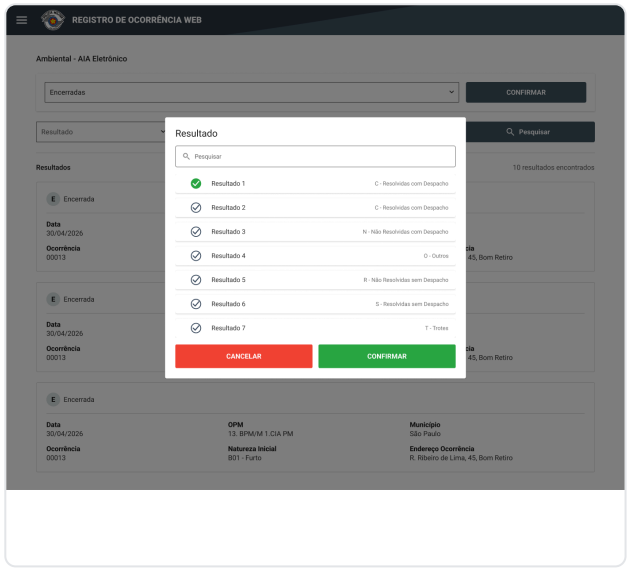
Web 1440px
3 a 6 h manuais

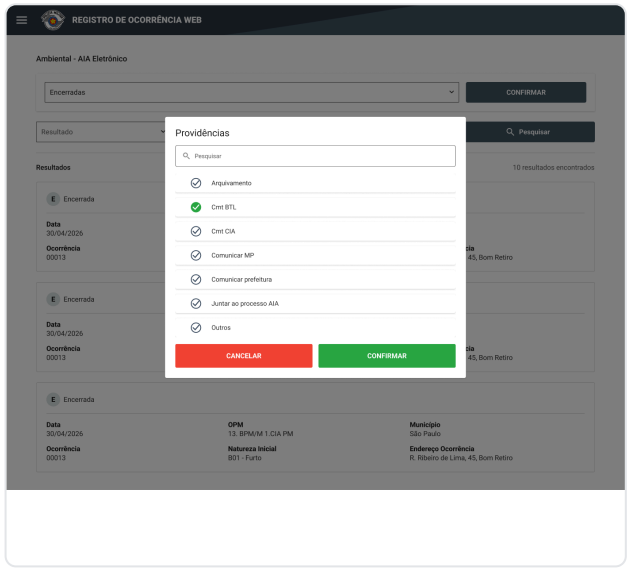








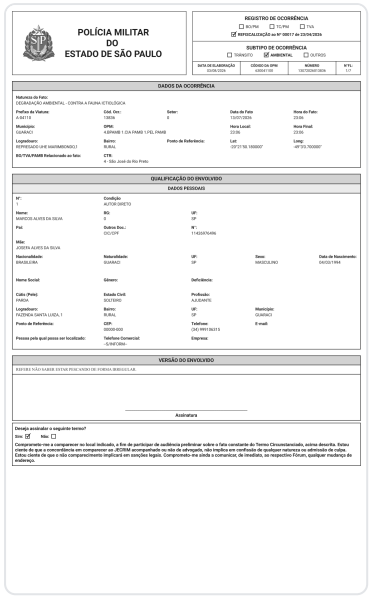




PBI 95903 · 10 PÁGINAS

PDF da Ocorrência Ambiental atualizado

Documento A4
5 a 10 h manuais



POLÍCIA MILITAR DO ESTADO DE SÃO PAULO

REGISTRO DE OCORRÊNCIA

☐ BO/PM ☐ TC/PM ☐ TVA

☑ REPESCAGEM ao Nº 00017 de 23/04/2026

SUBTIPO DE OCORRÊNCIA

☐ TRÂNSITO ☑ AMBIENTAL ☐ OUTROS

DATA DE ELABORAÇÃO	CÓDIGO DA OPM	NÚMERO	NTL
03/08/2026	4260/4/100	1067/2026/1380bi	1/1

DADOS DA OCORRÊNCIA

Natureza do Fato:
DEGRADAÇÃO AMBIENTAL - CONTRA A FAUNA ICTIOLÓGICA

Prefixo da Viatura:	Cód. Occ.:	Setor:	Data do Fato:	Hora do Fato:
A-94118	13836	6	13/07/2026	23:55
Município:	**DPM:**		**Hora Local:**	**Hora Final:**
GUARACI	4.BPAMB 1 CIA PAMB 1 PEL PAMB		23:55	23:55
Logradouro:	**Bairro:**	**Ponto de Referência:**	**Lat:**	**Long:**
REPESCADO (HE MARIMBONDO)	RURAL		-20°21'50.188000"	-48°25'2.780000"
BO/TVA/PAMB Relacionado ao fato:	**CTB:**			
	4 - São José do Rio Preto			

QUALIFICAÇÃO DO ENVOLVIDO

DADOS PESSOAIS

Nº:	Condição:		
1	AUTOR DIRETO		
Nome:	**RG:**	**UF:**	
MARCOS ALVES DA SILVA	0	SP	
Pai:	**Outros Doc.:**	**Nº:**	
	OC/CPF	11435476496	
Mãe:			
JOSEFA ALVES DA SILVA			
Nacionalidade:	**Naturalidade:**	**UF:**	**Sexo:**	**Data de Nascimento:**
BRASILEIRA	GUARACI	SP	MASCULINO	04/05/1994
Nome Social:	**Gênero:**	**Deficiência:**		
Cidade (Pelo):	**Estado Civil:**	**Profissão:**		
PARDA	SOLTEIRO	AJUDANTE		
Bairro:	**UF:**	**Município:**		
RURAL	SP	GUARACI		
Ponto de Referência:	**CEP:**	**Telefones:**		
	00000-000	(34) 99911 8613 9		
Pessoa pela qual possa ser localizado:	**Telefone Comercial:**	**Empresa:**		
	-5.5467.0894-			

VERSÃO DO ENVOLVIDO


RECUSE NÃO SABER ESTAR PENCANDO DE FORMA IRREGULAR.

Assinatura

Deseja assinalar o seguinte termo?
Sim ☑ Não ☐

Comprometo-me a comparecer no local indicado, a fim de participar de audiência preliminar sobre a fato constante do Termo Circunstanciado, sobre pena de desobediência. Estou ciente de que a ausência injustificada implicará em sanções legais. Comprometo-me ainda a comunicar, de imediato, ao respectivo Fórum, qualquer mudança de endereço.

Referente(s) Complementar(es)



POLÍCIA MILITAR DO ESTADO DE SÃO PAULO

REGISTRO DE OCORRÊNCIA

☐ BO/PM ☐ TC/PM ☐ TVA

☑ REPESCAGEM ao Nº 00017 de 23/04/2026

SUBTIPO DE OCORRÊNCIA

☐ TRÂNSITO ☑ AMBIENTAL ☐ OUTROS

DATA DE ELABORAÇÃO	CÓDIGO DA OPM	NÚMERO	NTL
03/08/2026	4260/4/100	1067/2026/1380bi	1/1

QUALIFICAÇÃO DO ENVOLVIDO

DADOS PESSOAIS

Nº:	Condição:		
2	AUTOR DIRETO		
Nome:	**RG:**	**UF:**	
LUCIANO PROCOPIO DA CRUZ	0	SP	
Pai:	**Outros Doc.:**	**Nº:**	
	OC/CPF	01915813584	
Mãe:			
CLEONICE BASILIA DARBOSA			
Nacionalidade:	**Naturalidade:**	**UF:**	**Sexo:**	**Data de Nascimento:**
BRASILEIRA	GUARACI	SP	MASCULINO	04/05/1994
Nome Social:	**Gênero:**	**Deficiência:**		
Cidade (Pelo):	**Estado Civil:**	**Profissão:**		
PARDA	SOLTEIRO	AJUDANTE		
Logradouro:	**Bairro:**	**UF:**	**Município:**	
FAZENDA SANTA LUZIA, 1	RURAL	SP	GUARACI	
Ponto de Referência:	**CEP:**	**Telefones:**	**E-mail:**	
	00000-000	(34) 98421-7294		
Pessoa pela qual possa ser localizado:	**Telefone Comercial:**	**Empresa:**		
	-5.5467.0894-			

VERSÃO DO ENVOLVIDO


RECUSE NÃO SABER ESTAR PENCANDO DE FORMA IRREGULAR.

Assinatura

Deseja assinalar o seguinte termo?
Sim ☐ Não ☐

Comprometo-me a comparecer no local indicado, a fim de participar de audiência preliminar sobre a fato constante do Termo Circunstanciado, sobre pena de desobediência. Estou ciente de que a ausência injustificada implicará em sanções legais. Comprometo-me ainda a comunicar, de imediato, ao respectivo Fórum, qualquer mudança de endereço.

Referente(s) Complementar(es)



POLÍCIA MILITAR DO ESTADO DE SÃO PAULO

ROTEIRO DE ACESSO

CROQUI

CARACTERIZAÇÃO DA DEGRADAÇÃO AMBIENTAL (ÁREA 1)

-20°21'50.18" -48°25'85.7"

CARACTERIZAÇÃO DA DEGRADAÇÃO AMBIENTAL (ÁREA 2)

-20°21'50.18" -48°25'85.7"

DADOS DA ÁREA (ÁREA 1)

Características da Área:
ÁREA RURAL - ÁREA PÚBLICA - RIO PERDIZ

Tipo de Infração Ambiental:
COMETER A FAUNA ICTIOLÓGICA - RES. SMA 85/17 - ART. 35 (II)**, INC.II

Tipo de Infração Ambiental:
PESCAR MEDIANTE A UTILIZAÇÃO DE APARELHOS, PETRECHOS, TÉCNICAS E MÉTODOS NÃO PERMITIDOS

Tipo de Penalidade:
PESCAR MEDIANTE A UTILIZAÇÃO DE

Complemento da Infração:
MÉTODOS NÃO PERMITIDOS

Detalhamento da Infração:
SEM DETALHAMENTO

Condicionantes: (Art. 3ºDECRETO 8.243/14-1)
POR CAUSA DO PRODUTO DA PESCARIA

Condicionantes: (Art. 3ºDECRETO 8.243/14-1)
- APREENSÃO
- MULTA SIMPLES (R$1.000,00)

Processos de Degradação:
Não se aplica

CARACTERIZAÇÃO AMBIENTAL DA ÁREA - MEIO FÍSICO (ÁREA 1)

Área Total em Hectares: 0,000000 **Área Degradada em Hectares:** 0,00000 **Tota de Arvores Isoladas por Unidade:** 0,00000

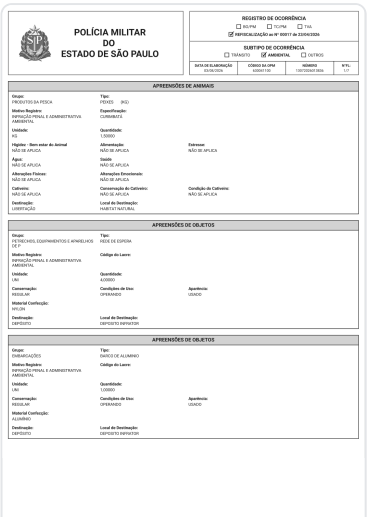
Relevo: Não se Aplica
Uso do Solo Não se Aplica
Características do Solo: Não se Aplica
Processos de Degradação: Não se Aplica

CARACTERIZAÇÃO DA DEGRADAÇÃO AMBIENTAL (ÁREA 1)

Infração contra a Fauna Ictiológica:
PESCAR MEDIANTE A UTILIZAÇÃO DE PESCAR MEDIANTE A UTILIZAÇÃO DE APARELHOS, PETRECHOS, TÉCNICAS E MÉTODOS NÃO PERMITIDOS

CARACTERIZAÇÃO DA DEGRADAÇÃO AMBIENTAL (ÁREA 2)

Infração contra a Fauna Ictiológica:
PESCAR MEDIANTE A UTILIZAÇÃO DE PESCAR MEDIANTE A UTILIZAÇÃO DE APARELHOS, PETRECHOS, TÉCNICAS E MÉTODOS NÃO PERMITIDOS



POLÍCIA MILITAR DO ESTADO DE SÃO PAULO

REGISTRO DE OCORRÊNCIA

☐ BO/PM ☐ TC/PM ☐ TVA

☑ REPESCAGEM ao Nº 00017 de 23/04/2026

SUBTIPO DE OCORRÊNCIA

☐ TRÂNSITO ☑ AMBIENTAL ☐ OUTROS

DATA DE ELABORAÇÃO	CÓDIGO DA OPM	NÚMERO	NTL
03/08/2026	4260/4/100	1067/2026/1380bi	1/1

APREENSÕES DE ANIMAIS


Grupo:	Tipo:	
PRODUTOS DA PESCA	PEIXES (KG)	
Motivo Registro:	**Especificação:**	
INFRAÇÃO PENAL E ADMINISTRATIVA AMBIENTAL	CURIMBATÁ	
Unidade:	**Quantidade:**	
KG	1,50000	
Higidez - Bom estar do Animal	**Alimentação**	**Extensor**
NÃO SE APLICA	NÃO SE APLICA	NÃO SE APLICA
Água:	**Sinais**	
NÃO SE APLICA	NÃO SE APLICA	
Alterações Físicas:	**Alterações Ambientais:**	
NÃO SE APLICA	NÃO SE APLICA	
Cativeiro:	**Conservação do Cativeiro:**	**Condição do Cativeiro:**
NÃO SE APLICA	NÃO SE APLICA	NÃO SE APLICA
Destinação:	**Local de Destinação:**	
LIBERTAÇÃO	HABITAT NATURAL	

APREENSÕES DE OBJETOS

Grupo:	Tipo:	
PETRECHOS, EQUIPAMENTOS E APARELHOS DE P	REDE DE ESPERA	
Motivo Registro:	**Código do Lavro:**	
INFRAÇÃO PENAL E ADMINISTRATIVA AMBIENTAL		
Unidade:	**Quantidade:**	
UNI	4,00000	
Conservação:	**Condições de Uso:**	**Apartência:**
REGULAR	OPERANDO	USADO
Material Confecção:		
NYLON		
Destinação:	**Local de Destinação:**	
EMPOSTO	DEPOSITO INFRATOR	

APREENSÕES DE OBJETOS

Grupo:	Tipo:	
EMBARCAÇÕES	BARCO DE ALUMÍNIO	
Motivo Registro:	**Código do Lavro:**	
INFRAÇÃO PENAL E ADMINISTRATIVA AMBIENTAL		
Unidade:	**Quantidade:**	
UNI	1,00000	
Conservação:	**Condições de Uso:**	**Apartência:**
REGULAR	OPERANDO	USADO
Material Confecção:		
ALUMÍNIO		
Destinação:	**Local de Destinação:**	
EMPOSTO	DEPOSITO INFRATOR	



POLÍCIA MILITAR DO ESTADO DE SÃO PAULO

REGISTRO DE OCORRÊNCIA

☐ BO/PM ☐ TC/PM ☐ TVA

☑ REPESCAGEM ao Nº 00017 de 23/04/2026

SUBTIPO DE OCORRÊNCIA

☐ TRÂNSITO ☑ AMBIENTAL ☐ OUTROS

DATA DE ELABORAÇÃO	CÓDIGO DA OPM	NÚMERO	NTL
03/08/2026	4260/4/100	1067/2026/1380bi	1/1


RELATÓRIO FOTOGRÁFICO

FOTO 1

FOTO 2

FOTO 3

FOTO 4



POLÍCIA MILITAR DO ESTADO DE SÃO PAULO

REGISTRO DE OCORRÊNCIA

☐ BO/PM ☐ TC/PM ☐ TVA

☑ REPESCALIZAÇÃO ao Nº 00017 de 23/04/2026

SUBTIPO DE OCORRÊNCIA

☐ TRÂNSITO ☑ AMBIENTAL ☐ OUTROS

DATA DE ELABORAÇÃO	CÓDIGO DA OPM	NÚMERO	NTL
03/08/2026	4260/4/100	1067/2026/1380bi	1/1

RELATÓRIO FOTOGRÁFICO

FOTO 5

ANEXOS DA OCORRÊNCIA

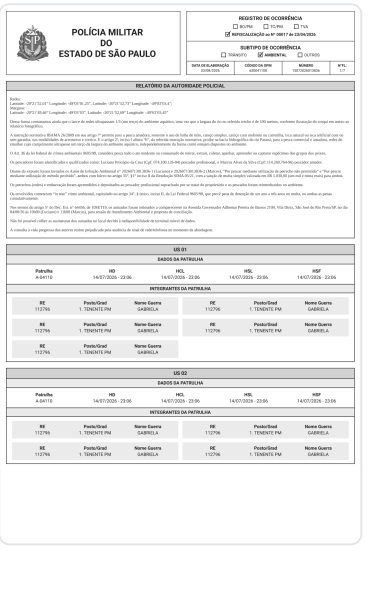
Seq.:	Nome Arquivo:	Descrição	Tipo:
1	130726_1		JPG
2	130726_2		JPEG
3	130726_3		JPEG
4	130726_4		JPEG
5	130726_5		JPEG
6	Boletim_Acesso_AM		JPG
7	Croqui_AM		JPG
8	SID_TCO_AIA_COMPLETO071435_1240_AM	Para Formalização	JPG
9	SID_TCO_AIA_COMPLETO071435_0825_AM	Prosseguir com oa; Encaminhe à PC com base artigo 34°, § único, inciso II, da Lei Federal 9605/98.	pdf

RELATÓRIO DA AUTORIDADE POLICIAL

Durante patrulhamento rotina, e deslocamento da operação "Amparo", na altura do viaduto Lauro para Bebedouro, uma equipe de policiamento ambiental composta pelo Cb PM Fabio, Cb PM Candido e Cb PM Thiabli, Vtr. A-84118 e embarcação A-04332, obteve a localização de pesca predatória no rio represado, montante da UHE de Marimbondo nesse tipo de Canoa/180

Foi decorrer do patrulhamento, em 13 de Julho de 2026, por volta das 10h00, abordamos 02 (dois) pescadores sendo 01 Lucio pescador profissional e 01 Lucil pescador amador realizando a pesca a na modalidade embarcado, a bordo de uma embarcação em dezoitenha sem marca aparente, sem os dizeres "Marcos R", matrícula 4G2013644, com uso de 04 (quatro) redes de espera em nylon duto, totalizando 200 metros de comprimento e malhas diversas, e até o momento havíamos capturado 02 exemplares da espécie "curimbatá" e 05 exemplares da espécie "Lucil", totalizando 2,5 kem e meio capturagemas.

Após minuciosa inversação dos coordenadas geográficas através do aplicativo "Fields Area Measure", e posteriore cheagem no "Google Earth", constatamos que a base de onde estava disposto no ambiente aquático do segundo momento.



POLÍCIA MILITAR DO ESTADO DE SÃO PAULO

REGISTRO DE OCORRÊNCIA

☐ BO/PM ☐ TC/PM ☐ TVA

☑ REPESCALIZAÇÃO ao Nº 00017 de 23/04/2026

SUBTIPO DE OCORRÊNCIA

☐ TRÂNSITO ☑ AMBIENTAL ☐ OUTROS

DATA DE ELABORAÇÃO	CÓDIGO DA OPM	NÚMERO	NTL
03/08/2026	4260/4/100	1067/2026/1380bi	1/1

RELATÓRIO DA AUTORIDADE POLICIAL

Kmhr:
Latitude: -20°21'53.01" Longitude: -48°25'38.25", Latitude: -20°21'52.79" Longitude: -48°25'53.8"),
Margem:
Latitude: -20°21'39.46" Longitude: -48°25'39.97", Latitude: -20°21'52.85" Longitude: -48°25'53.81"

Dessa forma constatamos ainda que o lance de rede ultrapassou 1.5 Cm (meio) do ambiente aquático, uma vez que a largura do rio no referido trecho é de 185 metros, conforme ilustração do croqui em anexo ao relatório fotográfico.

A instrução normativa IBAMA 26/2009 em seu artigo 7º permite para o para amadora, somente o uso de linha de mão, caniço simples, caniço com molinete ou carretilha, ica natural ou isca artificial com ou sem garateia, ou modalidades de arremesso e corrico, E o artigo 2º, inciso I, alínea "b", da referida instrução normativa, proíbe na bacia hidrográfica do rio Pranaí, para a pesca esportiva é amadora, redes de emalhar cujo comprimento ultrapasse um terço da largura do ambiente aquático, independentemente da forma como estejam dispostos no ambiente.

O Art. 36, II, da lei federal de crimes ambientais 9605/98, considera pesca todo o ato tendente ao consumado de retirar, extrair, coletar, apanhar, apreender ou capturar espécimes dos grupos dos peixes.

Os pescadores foram identificados e qualificados como: Lucinao Perolgio da Cruz (CPF: 019.183.126-06) pescador profissional, e Marcos Alves da Silva (CpF: 114.203.764-96) pescador amador.

Diante do exposto foram lavrados os Auto de Infração Ambiental nº 2026071.00.3836-1 (Lucinao) e 2026071.00.3836-2 (Marcos), "Por pescar mediante utilização de petrecho não permitido", e "Por pescar mediante utilização de método proibido", ambos com fulcro no artigo 35°, II° inciso II da Resolução SMA/85/17, com a sanção de multa simples valorada em R$ 1.038,00 para cada e multa multa para ambos.


Os petrechos foram identificados e apreendidos e depositados ao pescador profissional supracitado por se tratar de proprietário e os pescados foram remanescentes no ambiente

Os motivadores constantes "in natu" foram anilisados, capturado no artigo 34°, § único, inciso II, da Lei Federal 9605/98, que prevê pena de detenção de um ano a três meses, ou multa ou pena cumulativamente.

Nos termos do artigo 5° da Dec. Est. nº 66046, de 03/08/2721, os autuados foram intimados a comparecerem na Avenida Governador Adhemar Pereira de Barros 2100, Vila Dirce, São José do Rio Preto/SP, no dia 04/08/26 às 10h00 (cinco) e 13h00 (Marcos), para anuão do Atendimento Ambiental e propostas de conciliação.

Não foi possível colher os assinaturas dos autuados ou local devido à indisponibilidade de terminal móvel de dados.

A remedia à vida pregressa dos autores mesma prejudicada pela ausência de sinal de rede/telefonia no momento da abordagem.



POLÍCIA MILITAR DO ESTADO DE SÃO PAULO

REGISTRO DE OCORRÊNCIA

☐ BO/PM ☐ TC/PM ☐ TVA

☑ REPESCALIZAÇÃO ao Nº 00017 de 23/04/2026

SUBTIPO DE OCORRÊNCIA

☐ TRÂNSITO ☑ AMBIENTAL ☐ OUTROS

DATA DE ELABORAÇÃO	CÓDIGO DA OPM	NÚMERO	NTL
03/08/2026	4260/4/100	1067/2026/1380bi	1/1

ELABORADOR

14/07/2026 1290991.8 CB PM PIELMA

Data RE Posto / Graduação / Nome Guerra: Assinatura

COMANDANTE DA OPM/AMBI

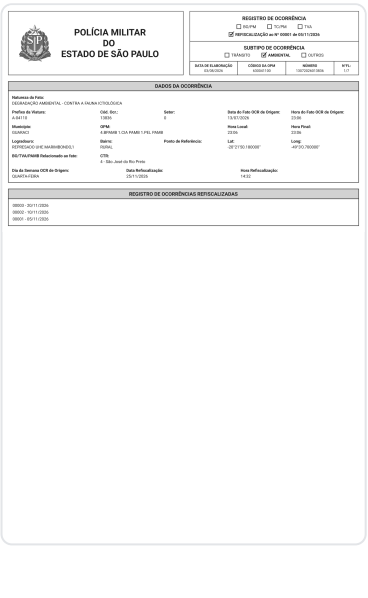
Providências Preliminares:
- ☐ Comunicar Polícia Judiciária
- ☐ Acompanhado
- ☐ Comunicar MP
- ☐ Juntar ao processo AIA

Remessa ao:
- ☐ CMT/UA
- ☐ Outros
- ☐ CMT BAT

Prosseguir com ao;
Encaminhar à PC com base artigo 34°, § único, inciso II, da Lei Federal 9605/98.

14/07/26 146804 1. TEN PM MACHADO

Data RE Posto / Graduação / Nome Guerra: Assinatura



POLÍCIA MILITAR DO ESTADO DE SÃO PAULO

REGISTRO DE OCORRÊNCIA

☐ BO/PM ☐ TC/PM ☐ TVA

☑ REPESCALIZAÇÃO ao Nº 00001 de 03/11/2026

SUBTIPO DE OCORRÊNCIA

☐ TRÂNSITO ☑ AMBIENTAL ☐ OUTROS

DATA DE ELABORAÇÃO	CÓDIGO DA OPM	NÚMERO	NTL
03/08/2026	4260/4/100	1067/2026/1380bi	1/1


DADOS DA OCORRÊNCIA

Natureza do Fato:
DEGRADAÇÃO AMBIENTAL - CONTRA A FAUNA ICTIOLÓGICA

Prefixo da Viatura:	Cód. Occ.:	Setor:	Data do Fato OCR de Origem:	Hora do Fato OCR de Origem:
A-94118	13836	6	13/07/2026	23:55
Município:	**DPM:**		**Hora Local:**	**Hora Final:**
GUARACI	4.BPAMB 1 CIA PAMB 1 PEL PAMB		23:55	23:55
Logradouro:	**Bairro:**	**Ponto de Referência:**	**Lat:**	**Long:**
REPESCADO (HE MARIMBONDO)	RURAL		-20°21'50.188000"	-48°25'2.780000"
BO/TVA/PAMB Relacionado ao fato:	**CTB:**			
	4 - São José do Rio Preto			
Dia da Semana OCR de Origem:	**Data Refocalização:**		**Hora Refocalização:**	
QUINTA-FEIRA	03/11/2026		14:22	

REGISTRO DE OCORRÊNCIAS REFOCALIZADAS

08/03 - 20/11/2026
08/03 - 10/11/2026
08/03 - 05/11/2026



POLÍCIA MILITAR DO ESTADO DE SÃO PAULO

REGISTRO DE OCORRÊNCIA

☐ BO/PM ☐ TC/PM ☐ TVA

☑ Refocalizada Vide RAPM

SUBTIPO DE OCORRÊNCIA

☐ TRÂNSITO ☑ AMBIENTAL ☐ OUTROS

DATA DE ELABORAÇÃO	CÓDIGO DA OPM	NÚMERO	NTL
03/08/2026	4260/4/100	1067/2026/1380bi	1/1

DADOS DA OCORRÊNCIA

Natureza do Fato:
DEGRADAÇÃO AMBIENTAL - CONTRA A FAUNA ICTIOLÓGICA

Prefixo da Viatura:	Cód. Occ.:	Setor:	Data do Fato:	Hora do Fato:
A-94118	13836	6	13/07/2026	23:55
Município:	**DPM:**		**Hora Local:**	**Hora Final:**
GUARACI	4.BPAMB 1 CIA PAMB 1 PEL PAMB		23:55	23:55
Logradouro:	**Bairro:**	**Ponto de Referência:**	**Lat:**	**Long:**
REPESCADO (HE MARIMBONDO)	RURAL		-20°21'50.188000"	-48°25'2.780000"
Município:	**DPM:**		**Hora Local:**	**Hora Final:**
GUARACI	4.BPAMB 1 CIA PAMB 1 PEL PAMB		23:55	23:55
Logradouro:	**Bairro:**	**Ponto de Referência:**	**Lat:**	**Long:**
REPESCADO (HE MARIMBONDO)	RURAL		-20°21'50.188000"	-48°25'2.780000"
BO/TVA/PAMB Relacionado ao fato:	**CTB:**			
	4 - São José do Rio Preto			

REGISTRO DE REFOCALIZAÇÃO

Ocorrência de Refocalização:
00004 DE 25/11/2026

POLÍCIA MILITAR DO ESTADO DE SÃO PAULO

REGISTRO DE OCORRÊNCIA

☐ BO/PM ☐ TC/PM ☐ TVA

☑ REPESCAGEM ao Nº 00017 de 23/04/2026

SUBTIPO DE OCORRÊNCIA

☐ TRÂNSITO ☑ AMBIENTAL ☐ OUTROS

DATA DE ELABORAÇÃO	CÓDIGO DA OPM	NÚMERO	NTL
03/08/2026	4260/4/100	1067/2026/1380bi	1/1

US 01

DADOS DA PATRULHA

Prefixo	HO	HOL	HSL	HSF
A-94118	14/07/2026 - 23:06	14/07/2026 - 23:06	14/07/2026 - 23:06	14/07/2026 - 23:06

INTEGRANTES DA PATRULHA

RE	Posto/Grad	Nome Guerra	RE	Posto/Grad	Nome Guerra
112796	1. TENENTE PM	GABRIELA	112796	1. TENENTE PM	GABRIELA
RE	Posto/Grad	Nome Guerra	RE	Posto/Grad	Nome Guerra
112796	1. TENENTE PM	GABRIELA	112796	1. TENENTE PM	GABRIELA
RE	Posto/Grad	Nome Guerra			
112796	1. TENENTE PM	GABRIELA			

US 02

DADOS DA PATRULHA

Prefixo	HO	HOL	HSL	HSF
A-94118	14/07/2026 - 23:06	14/07/2026 - 23:06	14/07/2026 - 23:06	14/07/2026 - 23:06

INTEGRANTES DA PATRULHA

RE	Posto/Grad	Nome Guerra	RE	Posto/Grad	Nome Guerra
112796	1. TENENTE PM	GABRIELA	112796	1. TENENTE PM	GABRIELA
RE	Posto/Grad	Nome Guerra			
112796	1. TENENTE PM	GABRIELA			